TrailSearch

Produktová dokumentace

Brtna Matouš
16.12.2023

1. Úvod

TrailSearch vznikl za důvodem ulehčení vyhledávání nových míst cyklistům v celém Česku. Jedná se o web, na který uživatelé mohou vyhledávat nové místa o kterých nevěděli a také komentovat místa, na kterých už naopak byli.

2. Struktura

Hlavní náplní této aplikace jsou jednotlivé stránky s traily. Jako první uživatel vstoupí na domovskou stranu, kde se nachází krátké info o této stránce, následně si bude moc vybrat z jaký trail si bude chtít prohlížet z navigace umístěné v levé části stránky. Pokud se však první bude chtít přihlásit, klikne na tlačítka registrovat nebo přihlásit v pravém horním rohu. Po kliknutí na tlačítko bude zobrazen daný formulář.

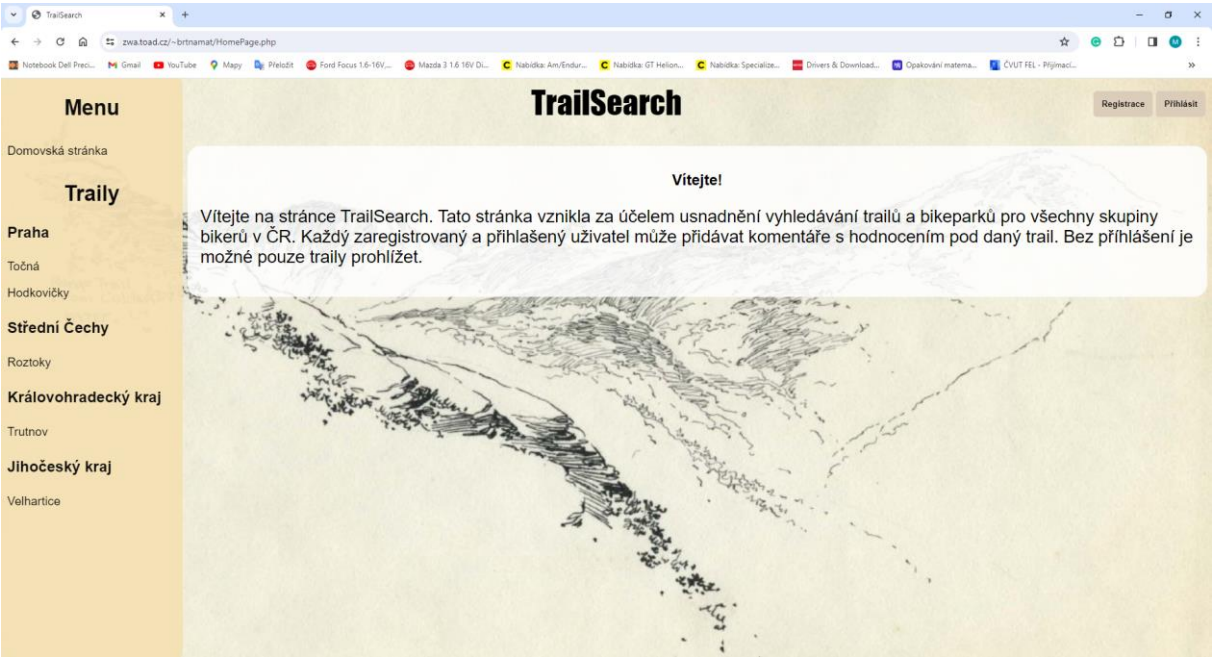

3. Uživatelé

Uživatelé webové aplikace se dělí na 3 typy (nepřihlášený, standartní uživatel a admin). Každý z nich má pak následně jiná práva.

Nepřihlášený: Může pouze prohlížet traily a k nim přidané komentáře

Standartní uživatel: Může prohlížet traily a vkládat komentáře pod jednotlivé traily. Své komentáře může i mazat.

Admin: Může vše co standartní uživatel, ale komentáře může mazat i cizí.

4. Registrace

Uživatel, který si bude chtít vytvořit účet se může registrovat pomocí registračního formuláře. Zde je nutné vyplnit uživatelské jméno, které je dlouhé alespoň 5 znaků a zvolit si heslo. Formulář následně obsahuje pole jméno a příjmení, která jsou však nepovinná. Po správném vyplnění bude uživatel automaticky přihlášen

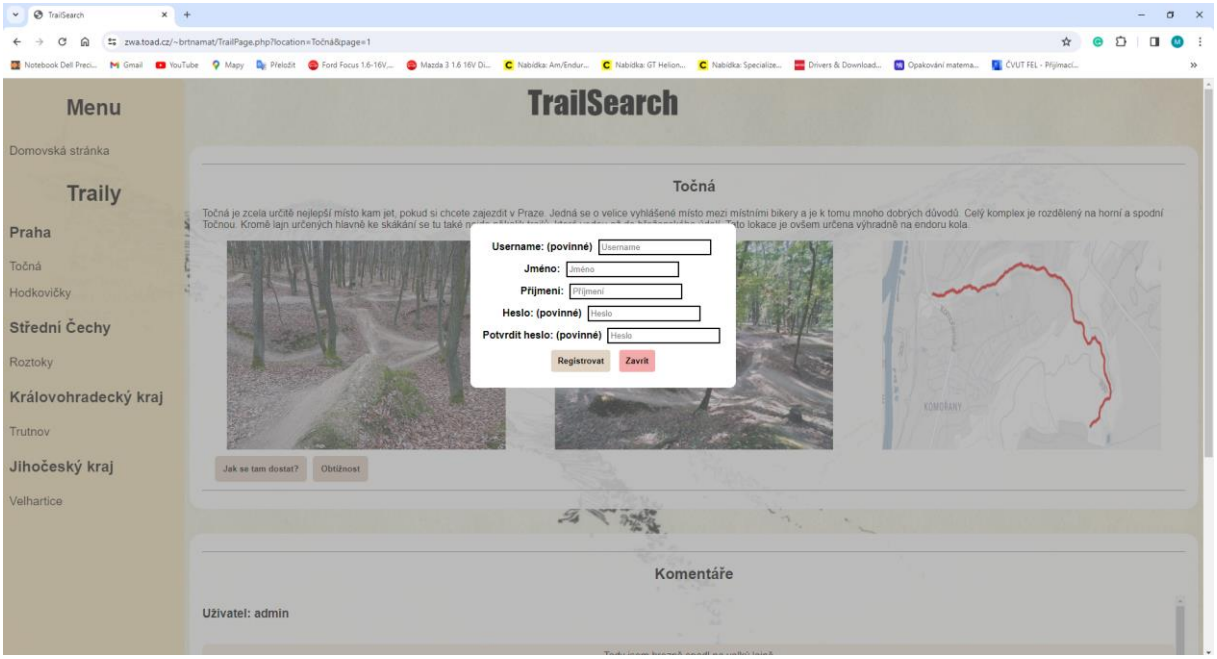

5. Přihlášení

Když se již registrovaný uživatel bude chtít přihlásit, využije pro to přihlašovací formulář kde stačí vyplnit pole uživatelské jméno a heslo.

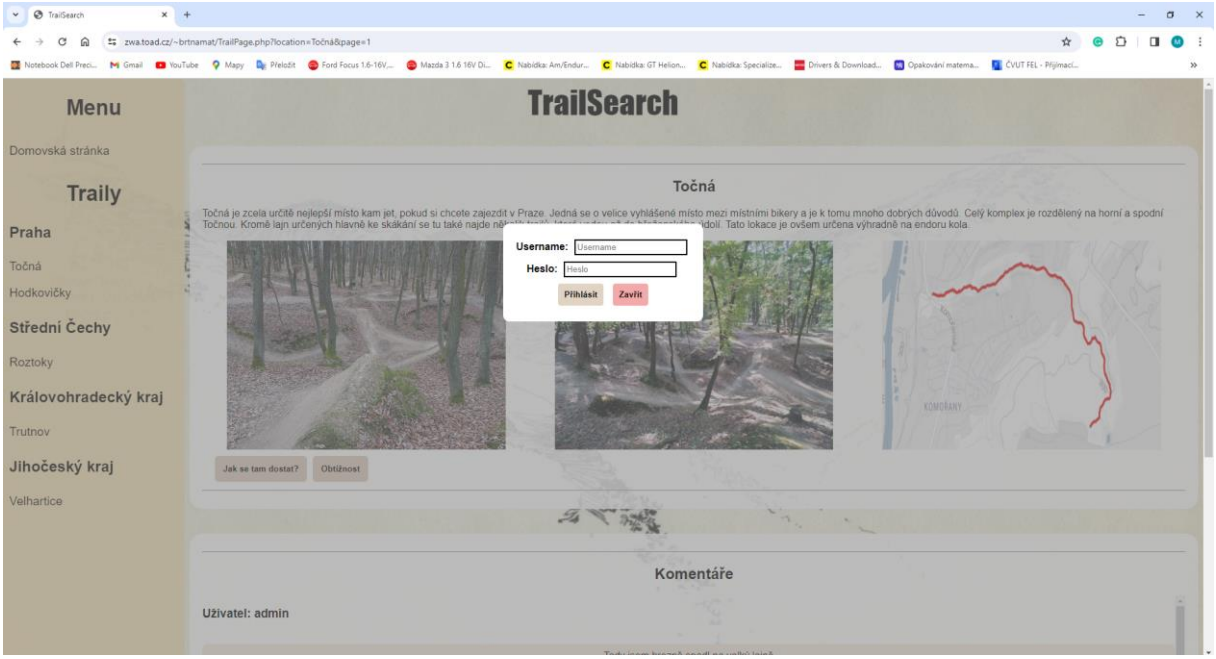

6. Úprava údajů

Až na uživatelské jméno jdou všechny údaje uživatele změnit právě uživatelem na profilové stránce. Kromě údajů z registračního formuláře je zde také profilová fotka kterou si uživatel může vybrat a nastavit. Tato fotka se zobrazuje na stránce jeho profilu. Na profilová stránka obsahuje také výpis všech uživatelem přidaných komentářů a možnost je mazat.

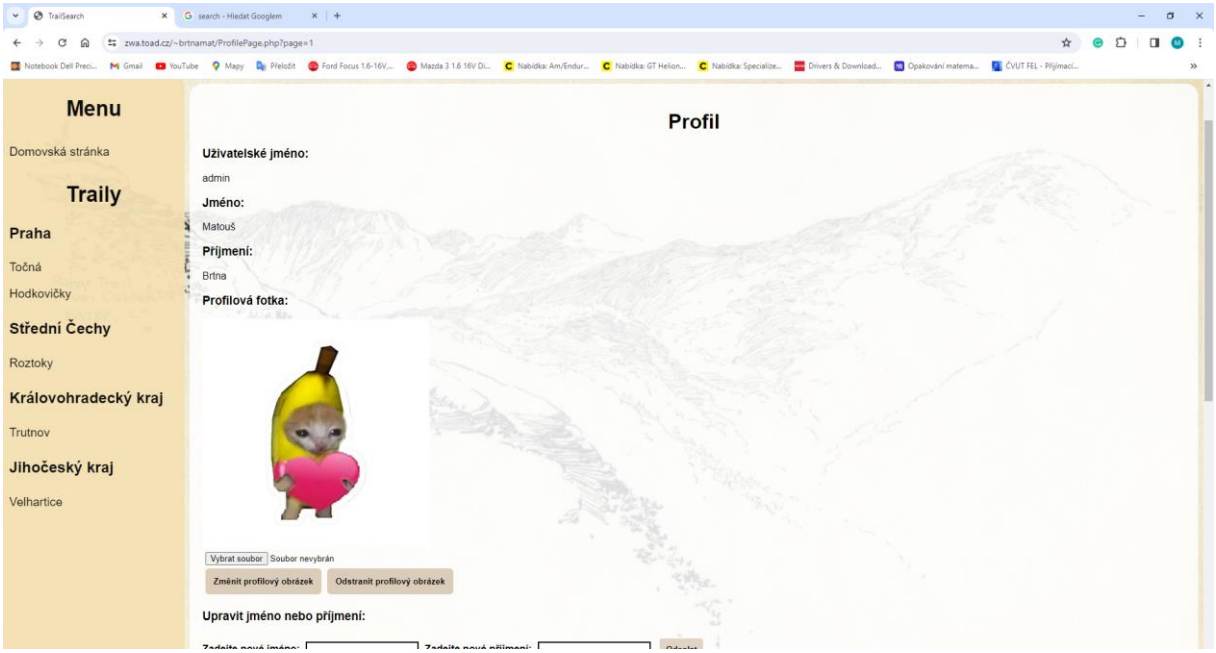

7. Stránka trailů

Každá trail má svou vlastní stránku, která obsahuje popisek o dané trase, tlačítko které po kliknutí sdělí informace o jeho obtížnosti a tlačítko s adresou a odkazem na Google maps. Pod popiskem jsou následně tři fotky z této lokace seznam uživateli přidaných komentářů rozdělených serverem na stránky po 10 komentářích. Pokud si tuto stránku zobrazuje přihlášený uživatel nebo admin a narazí na komentář, který má právo smazat, může ho smazat přímo zde

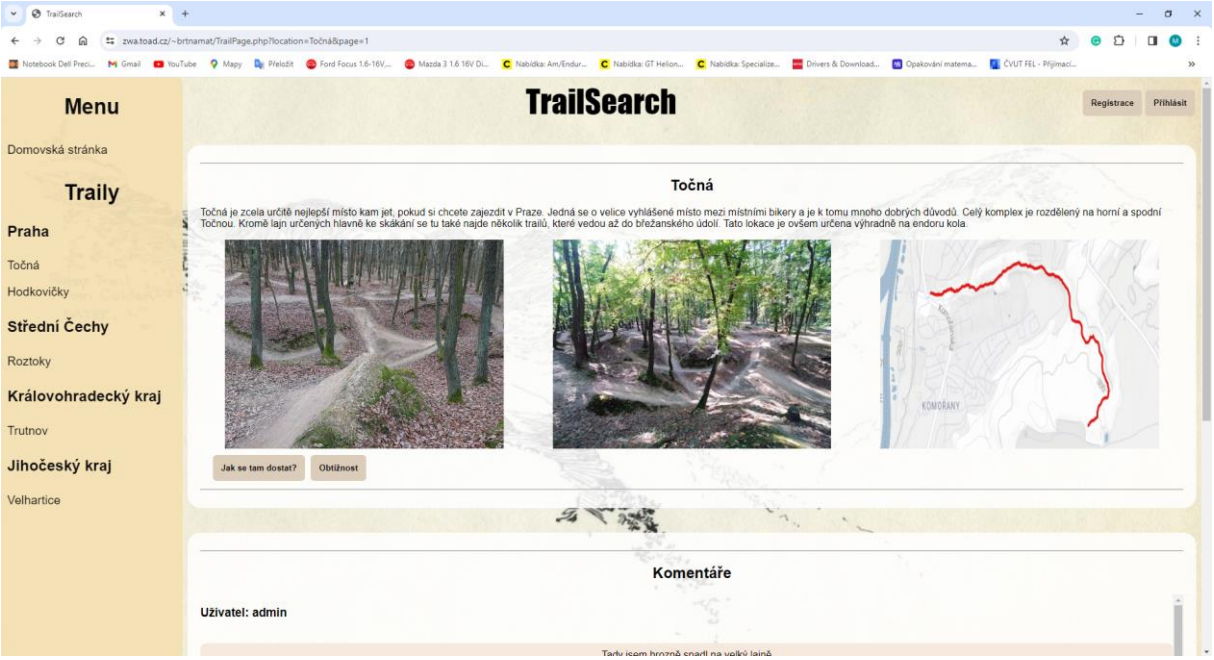

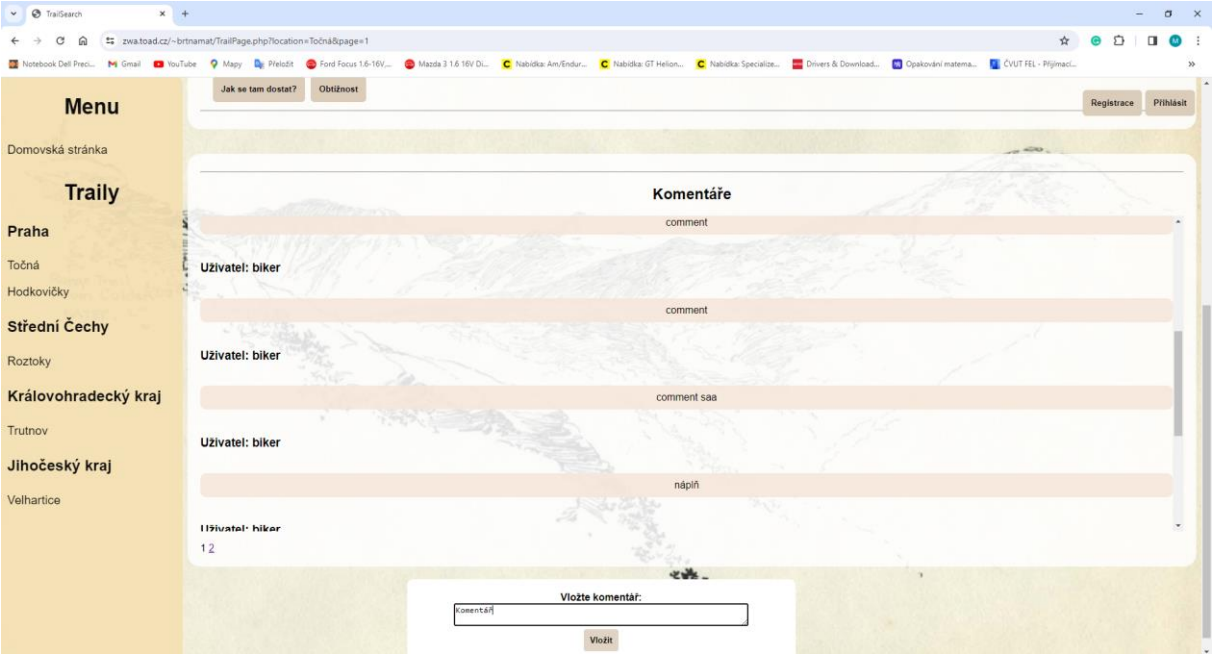
TrailSearch
zwa.toad.cz/~brtnamat/TrailPage.php?location=Točná&page=1
Menu
Domovská stránka
Traily
Praha
Točná
Hodkovičky
Střední Čechy
Roztoky
Královohradecký kraj
Trutnov
Jihočeský kraj
Velhartice
Jak se tam dostat?
Obtížnost
Registrace
Přihlásit
Komentáře
comment
Uživatel: biker
comment
Uživatel: biker
comment saa
Uživatel: biker
nápiři
Uživatel: biker
1 2
Vložte komentář:
Komentář
Vložit